# Sistem Informasi Geografis

## Tugas Praktikum 9

**Disusun Oleh :**

**M. Gymnastiar Syahputra (123140135)**

**Dosen Pengampu :**

**Muhammad Habib Algifari, S.Kom., M.TI**

**Alya Khairunnisa Rizkita, S.Kom., M.Kom**

**PROGRAM STUDI TEKNIK INFORMATIKA**

**FAKULTAS TEKNOLOGI INDUSTRI**

**INSTITUT TEKNOLOGI SUMATERA**

# Tugas 9

**Link Github** : https://github.com/gymnastiarsyahputra/Tugas-SIG_123140135.git

Deskripsi Tugas

Kembangkan aplikasi WebGIS full-stack dengan fitur autentikasi dan CRUD untuk mengelola data fasilitas publik di

wilayah Anda.

Ketentuan

- Backend: Implementasi CRUD lengkap dengan validasi Pydantic
- Auth: Implementasi login dengan JWT (minimal register & login)
- Frontend: Form untuk add/edit fasilitas dengan validasi
- Peta: Tampilkan marker yang bisa diklik untuk edit/delete
- Dokumentasi: README dengan cara setup dan screenshot

**Hasil :**

**Penambahan auth**

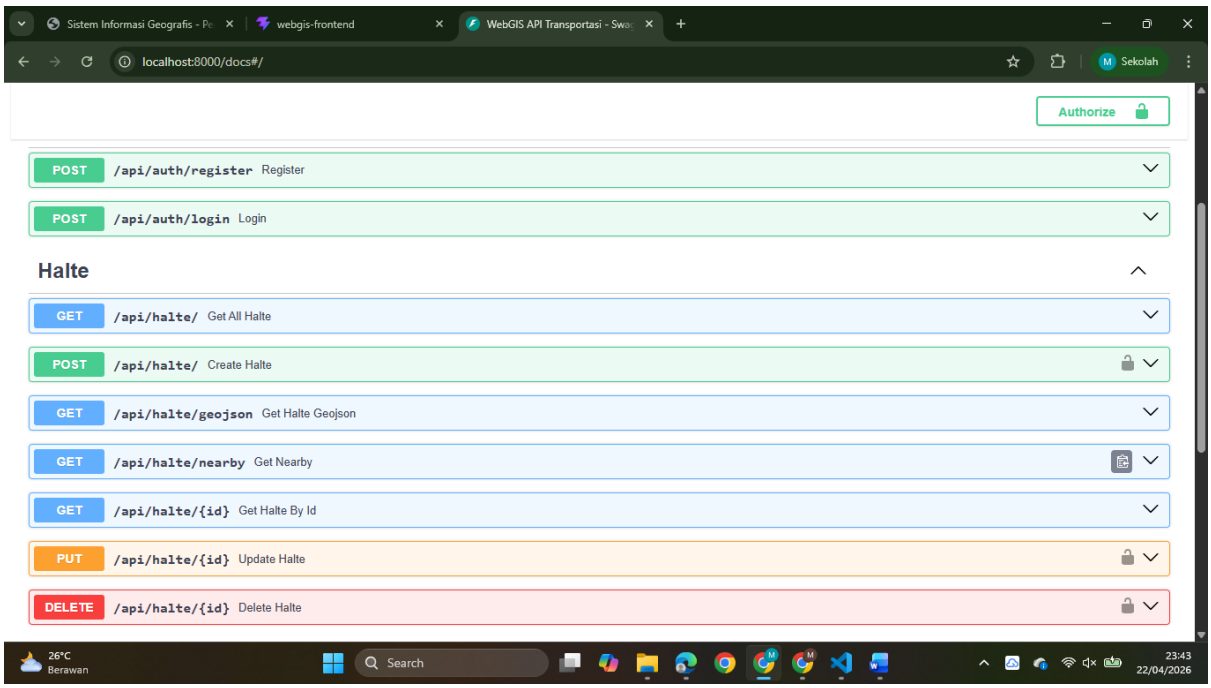
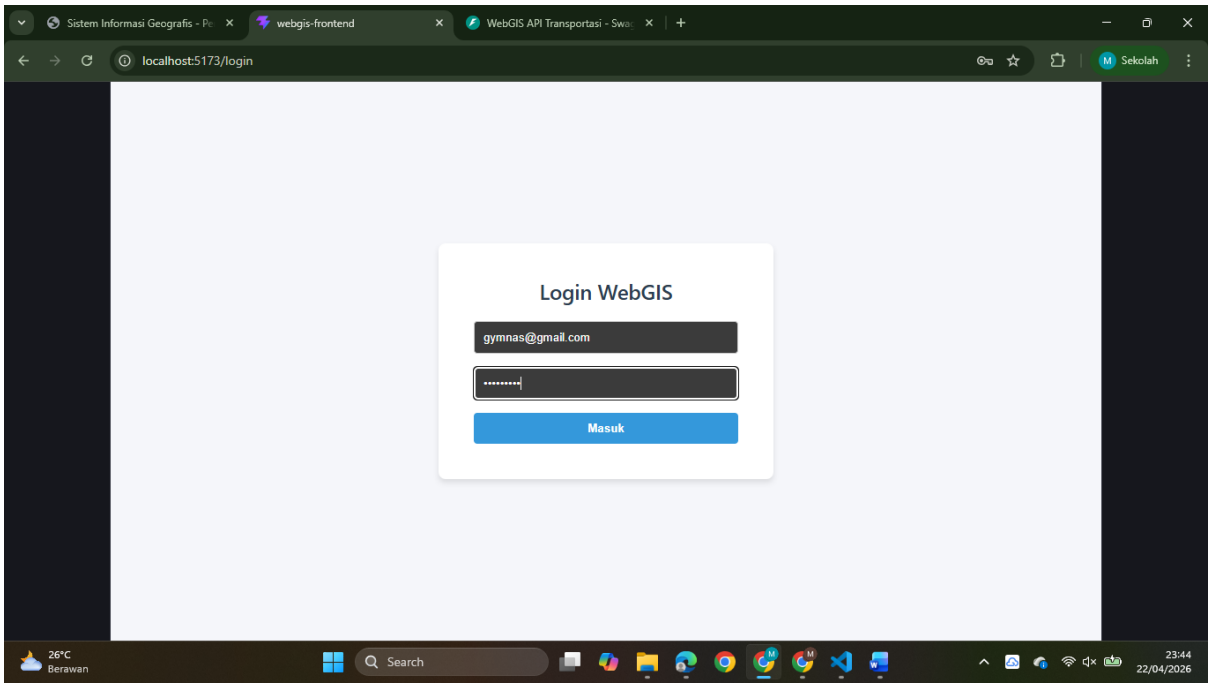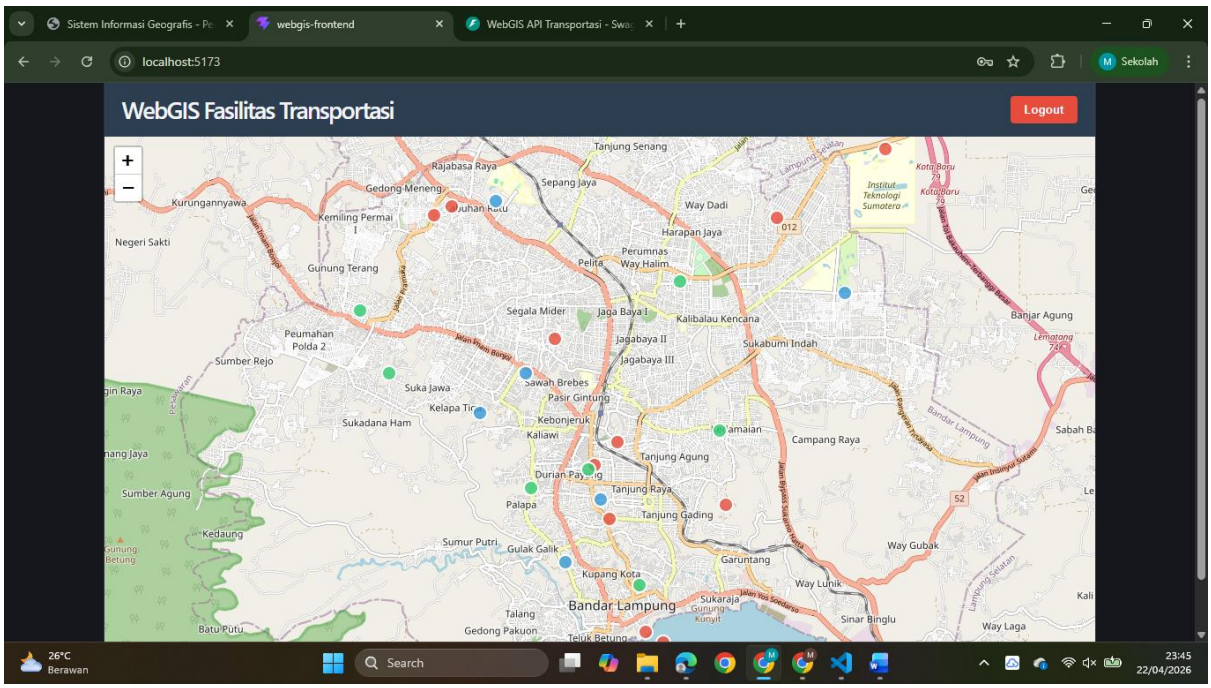
## Login dan Peta